Tiltaksanalyse
Nesodden kommune

Eiendom	3212 30/45		
Utskriftsdato	08.08.2024	**Antall datasett**	53

VIKTIG: Fravær av treff på et datasett betyr ikke nødvendigvis at området er fritatt for risiko, men at det ikke er gjort observasjoner av det aktuelle temaet i området, eller at området ikke er kartlagt. Treff på et datasett indikerer normalt at ytterligere undersøkelser er nødvendige.

Det tas forbehold om riktigheten eller fullstendigheten av opplysningene i dette dokumentet. Det kan ikke rettes krav som følge av at disse opplysningene benyttes som grunnlag for beslutninger.

12 Berørte datasett

- FKB-AR5
- Løsmasser N50/N250
- Mulighet for marin leire
- Overvannsanalyse 200-årsflom
- Overvannsanalyse 50-årsflom
- SSB - Arealbruk
- FKB-Bygning
- Marin grense
- Naturtyper i Norge - landskap
- Overvannsanalyse 20-årsflom
- Radon
- Tettsteder

41 Sjekkede, ikke berørte datasett

- Aktsomhetskart for snøskred
- Dybdedata
- Fiskeplasser redskap
- FKB-arealbruk
- Flom - aktsomhetsområder
- Foreslåtte naturvernområder
- Grunnvannsborehull
- Gyteområder
- Hoved- og biled, arealavgrensning
- Jordsmonn - Jordkvalitet
- Kulturlandskap - verdifulle
- Kulturminner - Lokaliteter, Enkeltminner og Sikringssoner
- Kvikkleire
- Mineralressurser - industrimineral, naturstein og metaller
- Naturtyper NiN etter Miljødirektoratets instruks
- Skredhendelser
- Statlige planretningslinjer for differensiert forvaltning av strandsonen langs sjøen
- Stormflo
- Trafikkmengde
- Turrutebasen
- Vannkraft, Utbygd og ikke utbygd
- Arter av nasjonal forvaltningsinteresse
- Dyrkbar jord
- FKB Tiltak
- FKB-Naturinfo
- Flom aktsomhetsområder - Nesodden
- Forurenset grunn
- Grus og pukk
- Hoved- og biled
- Jord- og flomskred, aktsomhetsområder
- Kartlagte og verdsatte friluftslivsområder
- Kulturminner – Fredete bygninger
- Kulturminner - SEFRAK
- Marine Naturtyper - DN håndbok 19
- Naturtyper - DN-håndbok 13
- Naturvernområder
- Statlig sikra friluftslivsområder
- Steinsprang - aktsomhetsområder
- Støykartlegging veg etter T-1442
- Trafikkulykker
- Utvalgte naturtyper

FKB-AR5

Kilde	Geovekst	Versjon	06.08.2024

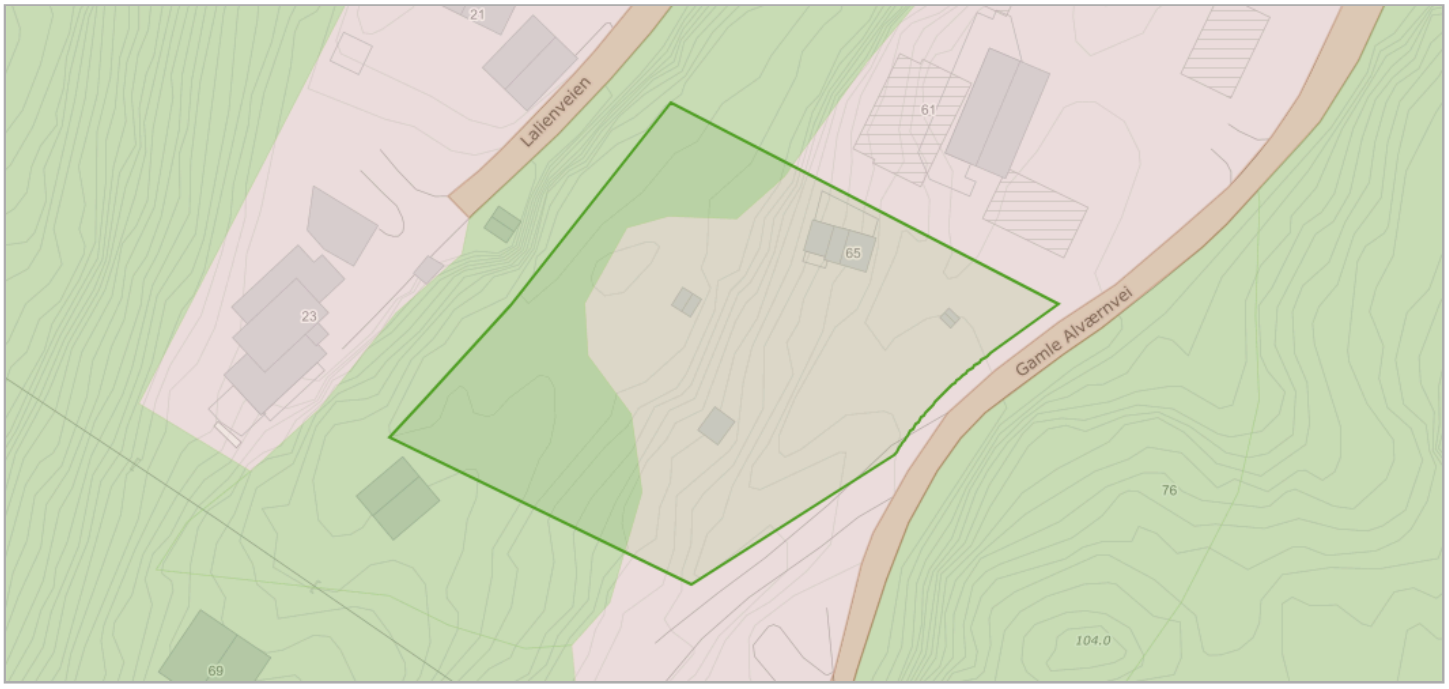

Om datasettet

FKB-AR5 beskriver Norges arealressurser i målestokk 1:5 000. AR5 vil danne grunnlag for videre ajourhold av detaljert arealressursinformasjon. AR5 er et flatedekkende datasett som er velegnet for analyseformål og kartframstillinger.

Tegnforklaring

- Bebyggelse
- Skog
- Samferdsel

Objekter

Arealtype	Grunnforhold	Skogbonitet	Treslag
Bebygd	Ikke relevant	Ikke relevant	Ikke relevant
Skog	Jorddekt	Impediment	Blandingsskog

FKB-Bygning

Kilde	Geovekst	Versjon	06.08.2024

Om datasettet

Datasettet viser bygninger fra FKB.

Objekter

Objekttype	Antall
annenbygning	3
veranda	2
bygning	1

Løsmasser N50/N250

Kilde	Norges geologiske undersøkelse	Versjon	12.03.2024

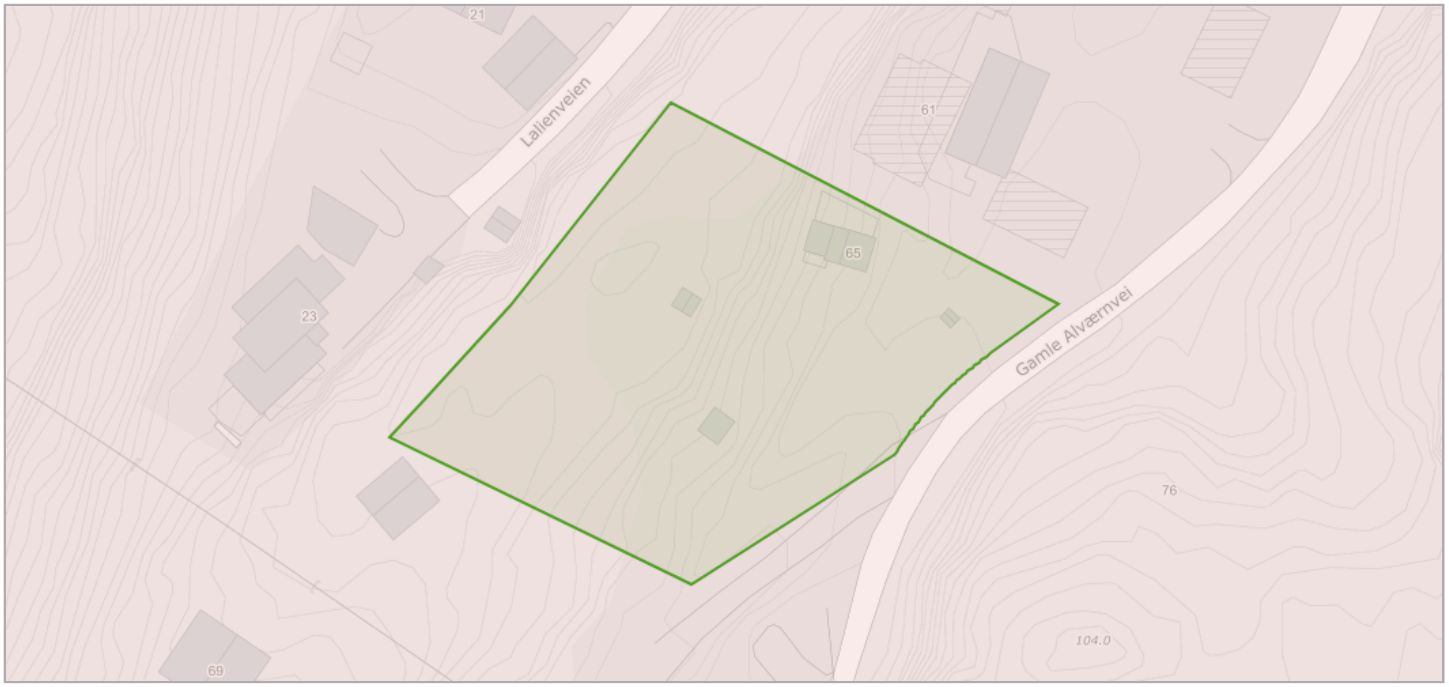

Om datasettet

Tegnforklaring

Løsmasser N50/N250
Bart fjell med tynt torvdekke

Datagrunnlaget for tema jordarter er basert på innholdet i kvartærgeologiske kart (løsmassekart), som foreligger analogt i flere målestokker (hovedsaklig M 1:50.000). Kartene er konvertert til digital form ved hjelp av skanning og vektorisering. I første omgang er kun flatene og formelementer (linjer) etablert som digitale datasett. Senere vil også punktinformasjonen bli tilgjengelig. Temakoder og egenskaper følger i hovedsak SOSI-standarden, versjon 4.0. I egenskapstabellen til kartet er det gitt opplysninger om jordartstype, og med utgangspunkt i jordartenes egenskaper er det utviklet avledede tema. Dette kan være infitrasjonsegenkaper og grunnvannspotensiale. Forholdene ligger også til rette for senere å utvikle tema av interesse for avfallsdeponering, grunnforhold og telefare. De avleda temaene må ikke oppfattes som absolutte, men er kun retningsgivende. Lokale forhold og variasjoner vil kunne medvirke til at avledningen burde være annerledes enn oppgitt. Lokale undersøkelser anbefales derfor før tiltak basert på avledningen settes i verk.

Objekter

Løsmassetype	Infiltrasjonsegenskap	Grunnvann
Bart fjell	Uegnet	Ikke grunnvannspotensial i løsmassene

Marin grense

Kilde	Norges geologiske undersøkelse	Versjon	07.08.2024

Om datasettet

Marin grense angir det høyeste nivået som havet nådde etter siste istid. Marin grense angir dermed det høyest mulige nivået for marine sedimenter (hav- og fjordavsetninger) som er hevet til tørt land. Dataene består av punktregistreringer, linjer samt polygoner. Linjer og polygoner er modellert fra punktene og en 10 m høydemodell.

Tegnforklaring

Marin grense flate
Marin grense flate

Mulighet for marin leire

Kilde	Norges geologiske undersøkelse	Versjon	09.07.2024

Om datasettet

Tegnforklaring

Mulighet for marin leire
Stort sett fraværende

Mulighet for marin leire er basert på løsmassekart i ulik målestokk og datasett for marin grense. Løsmassetyper under marin grense er klassifisert etter muligheten for å finne marin leire og kan grovt sett inndeles i seks klasser. Karttjenesten 'Mulighet for marin leire' er opprettet som en hjelp til å lese et kvartærgeologisk kart. Datasettet kan brukes til overordnet "screening" av store områder mht mulig forekomst av marin leire. Andre type data kan bidra til å verifisere om hvorvidt marin leire er tilstede eller ikke, for eksempel grunnboringsdata.

Objekter

Mulig marin leire	Løsmassetype
stortSettFraværende	Bart fjell

Naturtyper i Norge - landskap

Kilde	Artsdatabanken	Versjon	07.08.2024

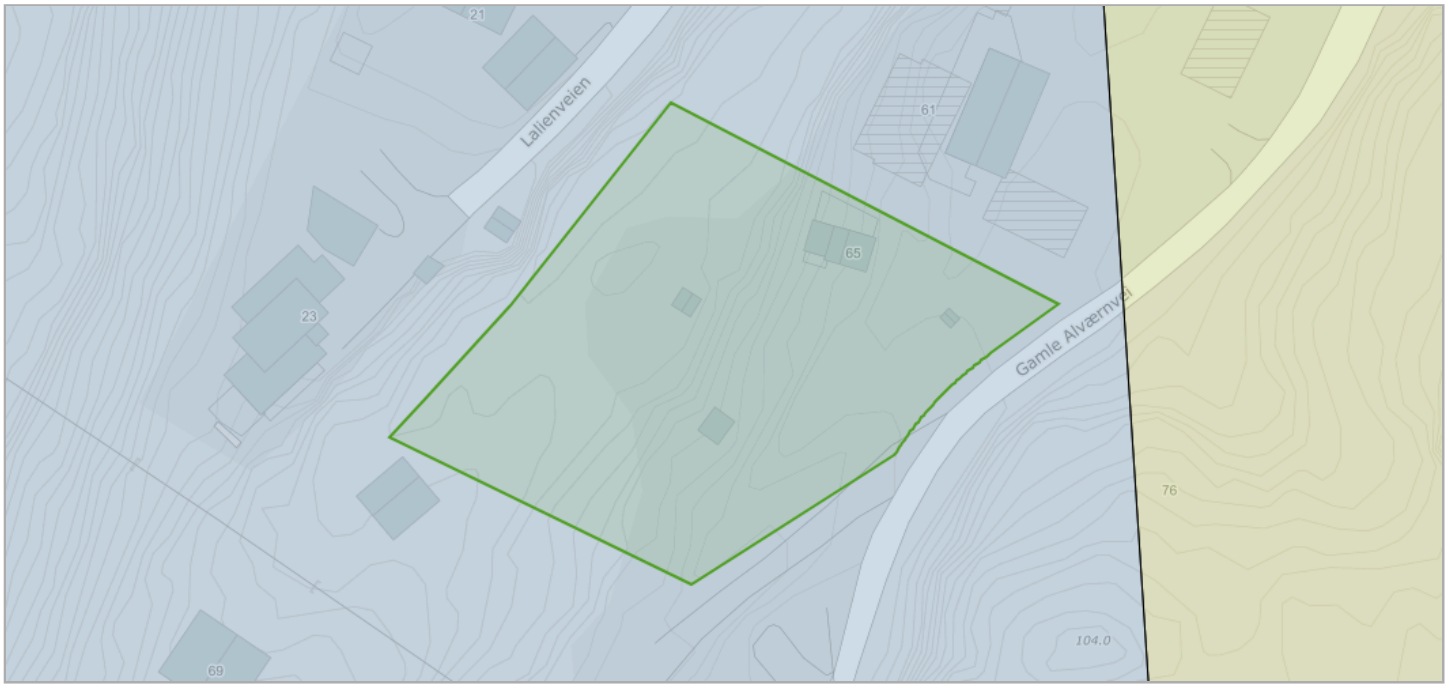

Om datasettet

NiN landskap er et system for beskrivelse av landskapsmessig variasjon som forholder seg til definisjonene i den europeiske landskapskonvensjonen og i naturmangfoldloven. NiN landskap er en del av Artsdatabanken sitt typesystem «Natur i Norge (NiN)». Kartleggingsmetodikken er utviklet for Nordland fylke, og standarden er utviklet etter et pilotprosjekt i Nordland fylke. Systemet inneholder standardisert metodikk for avgrensing og typeinndeling av landskap. Landskapsnivået i NiN er tilpasset kartlegging i målestokk 1:50 000. Landskapstypeinndelingen i NiN omfatter alle landskap fra naturlandskap, via jordbrukslandskap til bylandskapet. På grunnlag av digitale terrengformanalyser er det laget standardiserte kriterier for inndeling i hovedtyper og grupper av hovedtyper, som fanger opp variasjonen i landskapet på grov skala. Videre er det utarbeidet en typeinndeling for å adressere landskapsvariasjon i finere skala basert på variasjon i landskapets innhold og egenskaper. Variasjon i landskapet langs ti gradienter danner grunnlag for denne inndelingen.

Tegnforklaring

Innland - ås og fjellandskap
- Innland - ås og fjellandskap

Kyst - slettelandskap
- Kyst - slettelandskap

Objekter

Objekttype	Kode	Landskapstype
kyst_slettelandskap	LA-TI-K-S	Skjermet indre slakt til småkupert kystslettelandskap med tett bebyggelse

Overvannsanalyse 200-årsflom

Kilde	Nesodden kommune	Versjon	14.05.2024

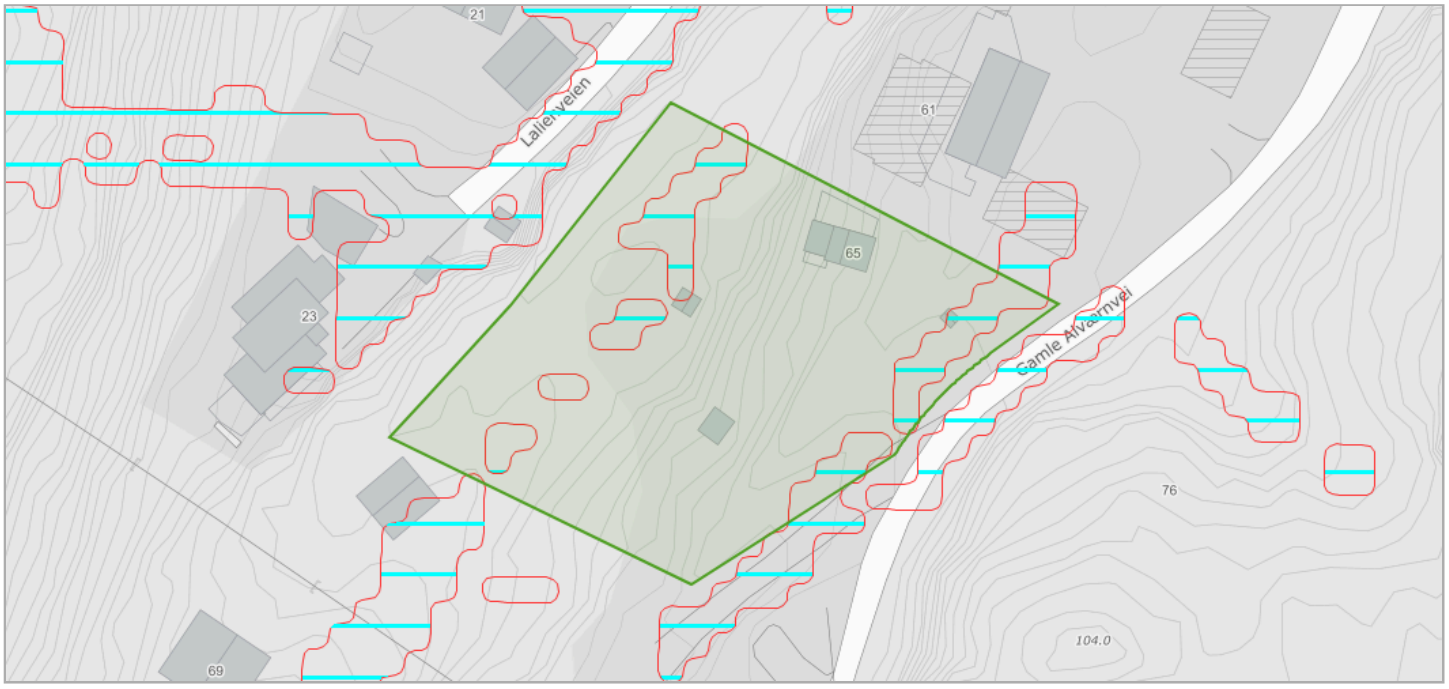

Om datasettet

Tegnforklaring

Flommodellering utført av Multiconsult på oppdrag fra Nesodden kommune. Simuleringer er gjort for nedbørshendelser med gjentaksintervall på 200 år, tillagt en klimafaktor på 1,5. Modelleringen er gjort ved bruk av Mike-programvare. Kartleggingen er gjort på et overordnet nivå (cellestørrelse på 3 x 3 meter i modellene) og viser lokaliteter der store vannmengder samler seg. Resultatene må ikke benyttes ukritisk som detaljinformasjon for videre bruk. Det er forhold, blant annet sluk og mindre ledninger, som påvirker avrenningen, og som ikke er lagt inn i modellen. Vannhøyde under 20 cm er tatt ut.

Overvannsanalyse 20-årsflom

Kilde	Nesodden kommune	Versjon	14.05.2024

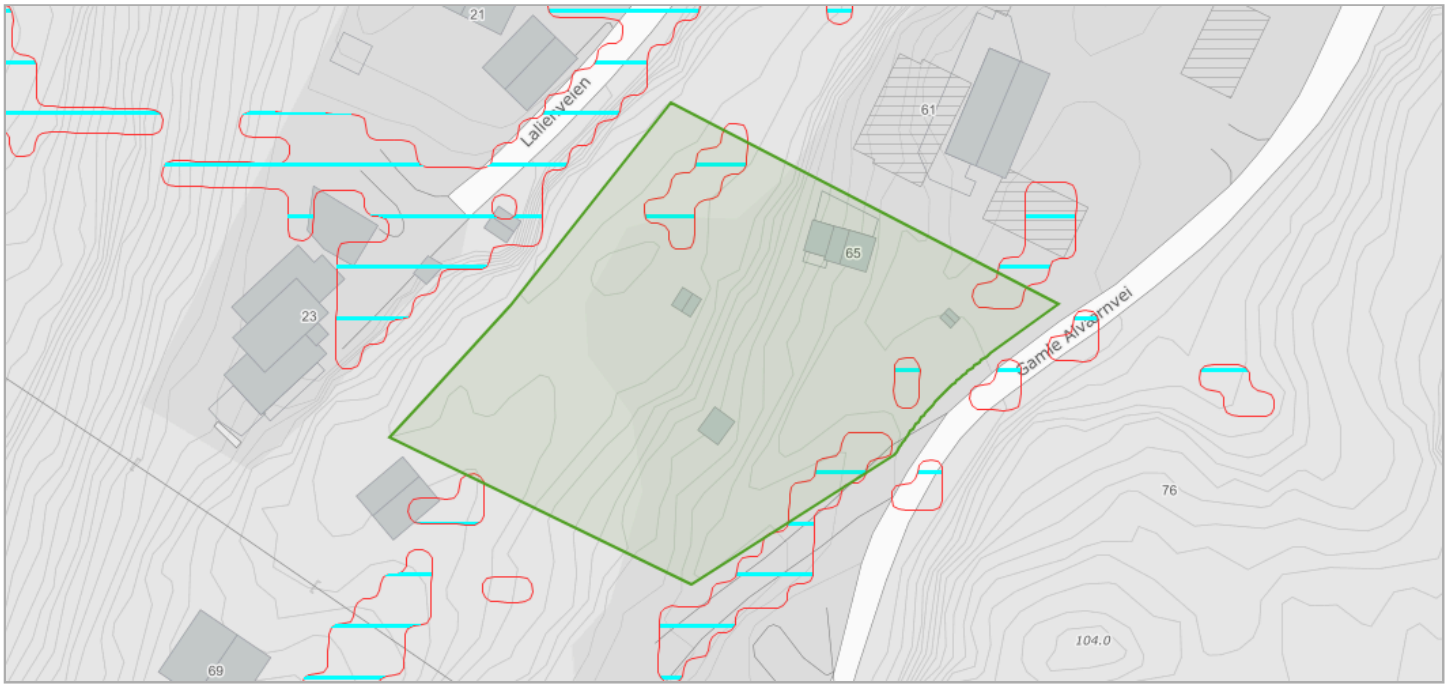

Om datasettet

Tegnforklaring

Flommodellering utført av Multiconsult på oppdrag fra Nesodden kommune. Simuleringer er gjort for nedbørshendelser med gjentaksintervall på 20 år, tillagt en klimafaktor på 1,5. Modelleringen er gjort ved bruk av Mike-programvare. Kartleggingen er gjort på et overordnet nivå (cellestørrelse på 3 x 3 meter i modellene) og viser lokaliteter der store vannmengder samler seg. Resultatene må ikke benyttes ukritisk som detaljinformasjon for videre bruk. Det er forhold, blant annet sluk og mindre ledninger, som påvirker avrenningen, og som ikke er lagt inn i modellen. Vannhøyde under 20 cm er tatt ut.

Overvannsanalyse 50-årsflom

Kilde	Nesodden kommune	Versjon	14.05.2024

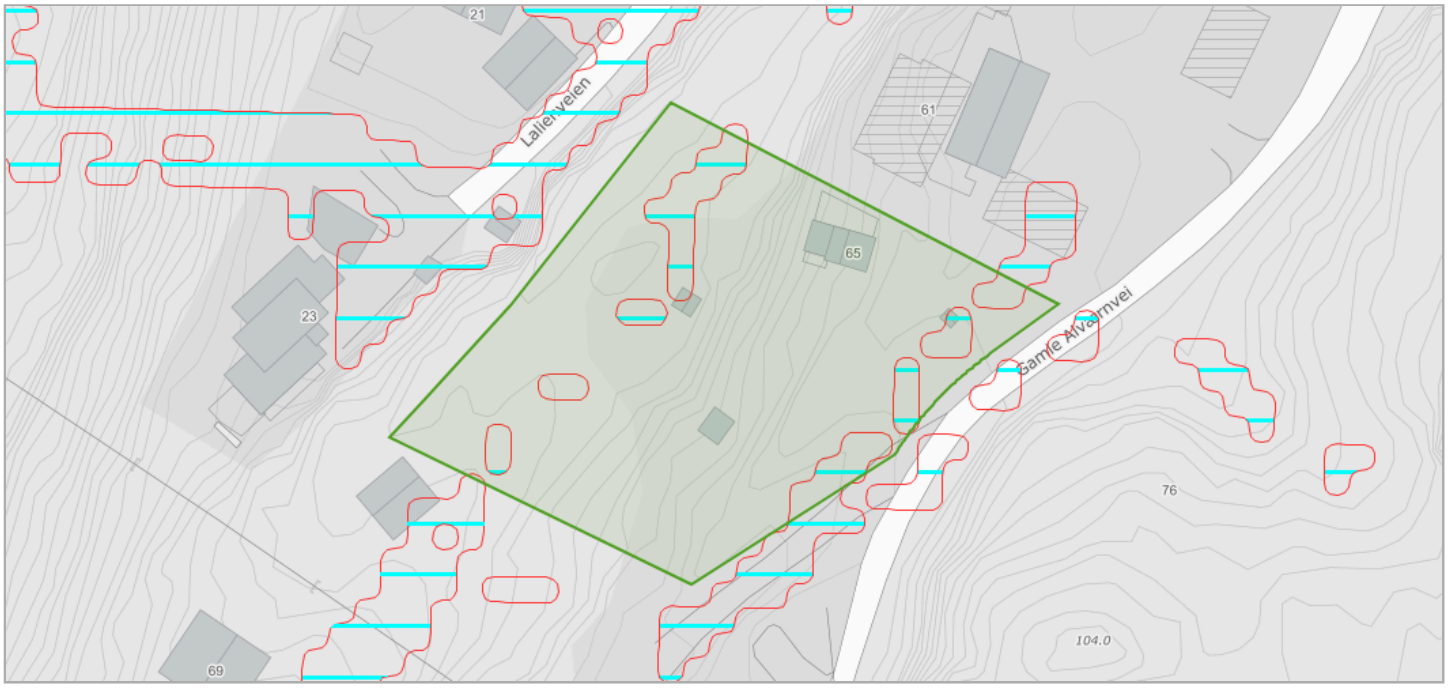

Om datasettet

Tegnforklaring

Flommodellering utført av Multiconsult på oppdrag fra Nesodden kommune. Simuleringer er gjort for nedbørshendelser med gjentaksintervall på 50 år, tillagt en klimafaktor på 1,5. Modelleringen er gjort ved bruk av Mike-programvare. Kartleggingen er gjort på et overordnet nivå (cellestørrelse på 3 x 3 meter i modellene) og viser lokaliteter der store vannmengder samler seg. Resultatene må ikke benyttes ukritisk som detaljinformasjon for videre bruk. Det er forhold, blant annet sluk og mindre ledninger, som påvirker avrenningen, og som ikke er lagt inn i modellen. Vannhøyde under 20 cm er tatt ut.

Radon

Kilde	Norges geologiske undersøkelse	Versjon	15.06.2020

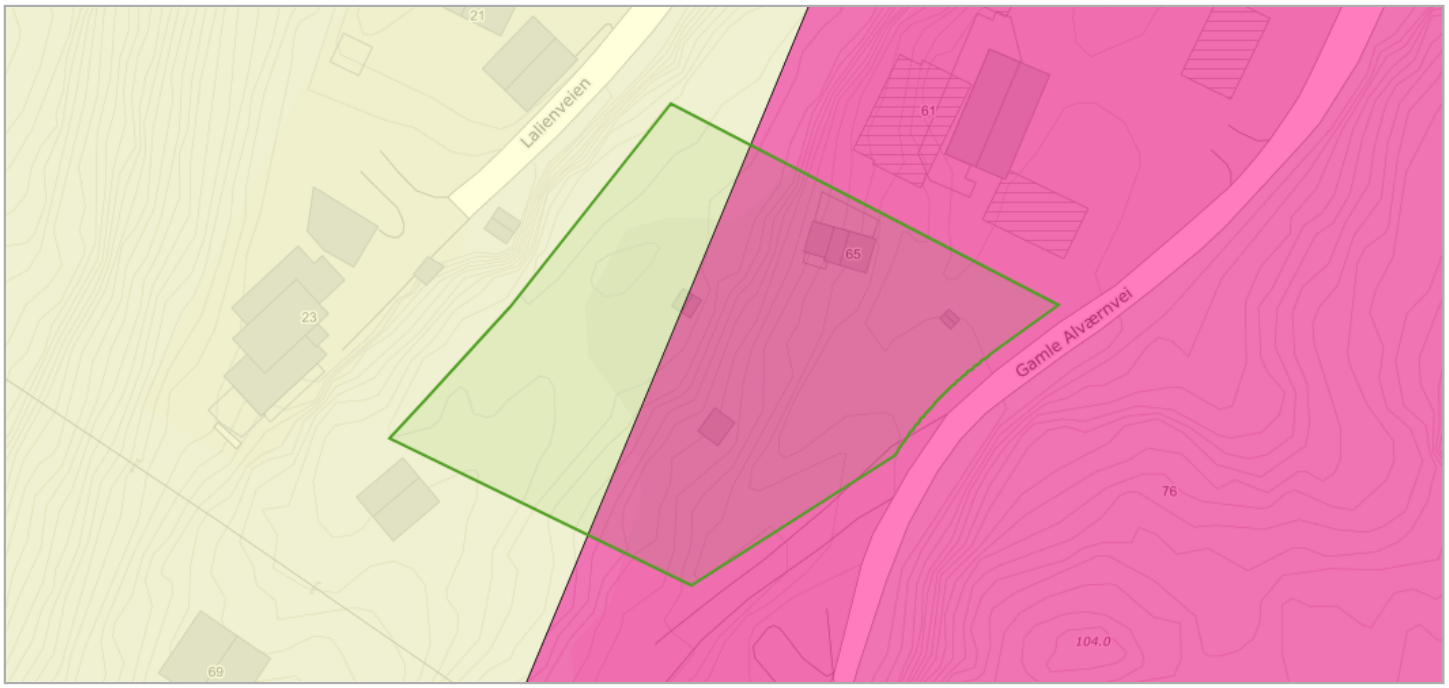

Om datasettet

Tegnforklaring

Radon aktsomhetsområde
- Moderat til lav
- Høy

Datasettet viser hvilke områder i Norge som trolig er mer radonutsatt enn andre. Datasettet er basert på geologi og inneluftsmålinger av radon. Inneluftsmålinger er fra NRPA sin nasjonale database, og geologi er fra NGU sine berggrunns- og løsmassedatabaser. Berggrunnsdata er av målestokk 1:250.000 og løsmassedata er av varierende målestokk, fra 1:50.000 til 1:1000.000 Inneluftsmålinger er brukt til å identifisere områder med forhøyd aktsomhet for radon. De er også brukt til å kjennetegne geologi i forhold til aktsomhet for radon, og denne kunnskapen er overført til områder hvor det finnes ingen eller få inneluftsmålinger. Der hvor et område er klassifisert som «høy aktsomhet» er det beregnet at minst 20% av boligene har radonkonsentrasjoner over 200 Bq/m3, med 70% statistisk sikkerhet. Der hvor et område er klassifisert som «middels til lav aktsomhet» er det beregnet at opp til 20% av boligene har radonkonsentrasjoner over 200 Bq/m3, med 70% statistisk sikkerhet. Der hvor det ikke er nok data, eller hvor det ikke er nok statistisk sikkerhet for å beregne aktsomhet for radon, er områder klassifisert som «usikker aktsomhet». Alunskifer er tilknyttet forhøyde radonkonsentrasjoner. Områder hvor det finnes alunskifer er klassifisert som «særlig høy aktsomhet». Med å overføre kunnskap fra områder med inneluftsmålinger til områder uten inneluftsmålinger, er det antatt at radonegenskaper av en geologitype er det samme i hele landet. I praksis kan det forventes noe variasjon i radonegenskaper i polygoner av den samme geologitypen. I tillegg kan det forventes variasjon i radonegenskaper innenfor et polygon.

Objekter

Aktsomhetsgrad
Høy
Moderat til lav

SSB - Arealbruk

Kilde	Statistisk sentralbyrå	Versjon	04.08.2022

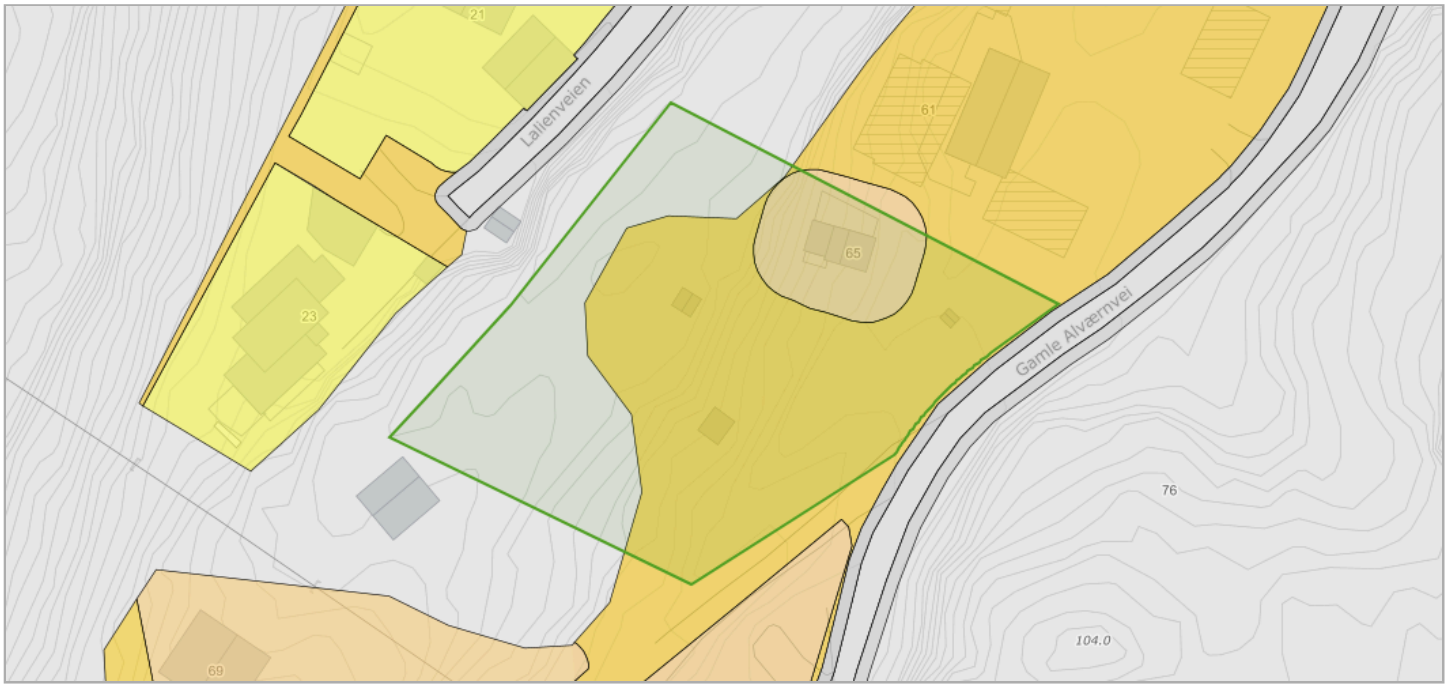

Om datasettet

SSB-arealbruk er sammensatt av registerinformasjon og en lang rekke kartgrunnlag, og viser arealbruksstatus for aktuelt år så fullstendig og detaljert som mulig. SSB-arealbruk er egnet til overvåking av utviklingen sett opp mot rådende nasjonale mål og retningslinjer. I tillegg kan den fungere som et informasjonsgrunnlag for utforming av nye nasjonale strategier. Det kan også være et kunnskapsgrunnlag i mer regionalt og lokalt planarbeid, og danne grunnlag for analyser.

Tegnforklaring

Arealbruk
- Boligbebyggelse
- Fritidsbebyggelse
- Transport og telekommunikasjon
- Uklassifisert bebyggelse og anlegg

Objekter

Underklasse	Hovedklasse	Kilde
UklassifisertBeb	UklassifisertBeb	Ar5
FritidsBeb	Fritidsbebyggelse	BebygdBufferSsb

Tettsteder

Kilde	Statistisk sentralbyrå	Versjon	07.08.2024

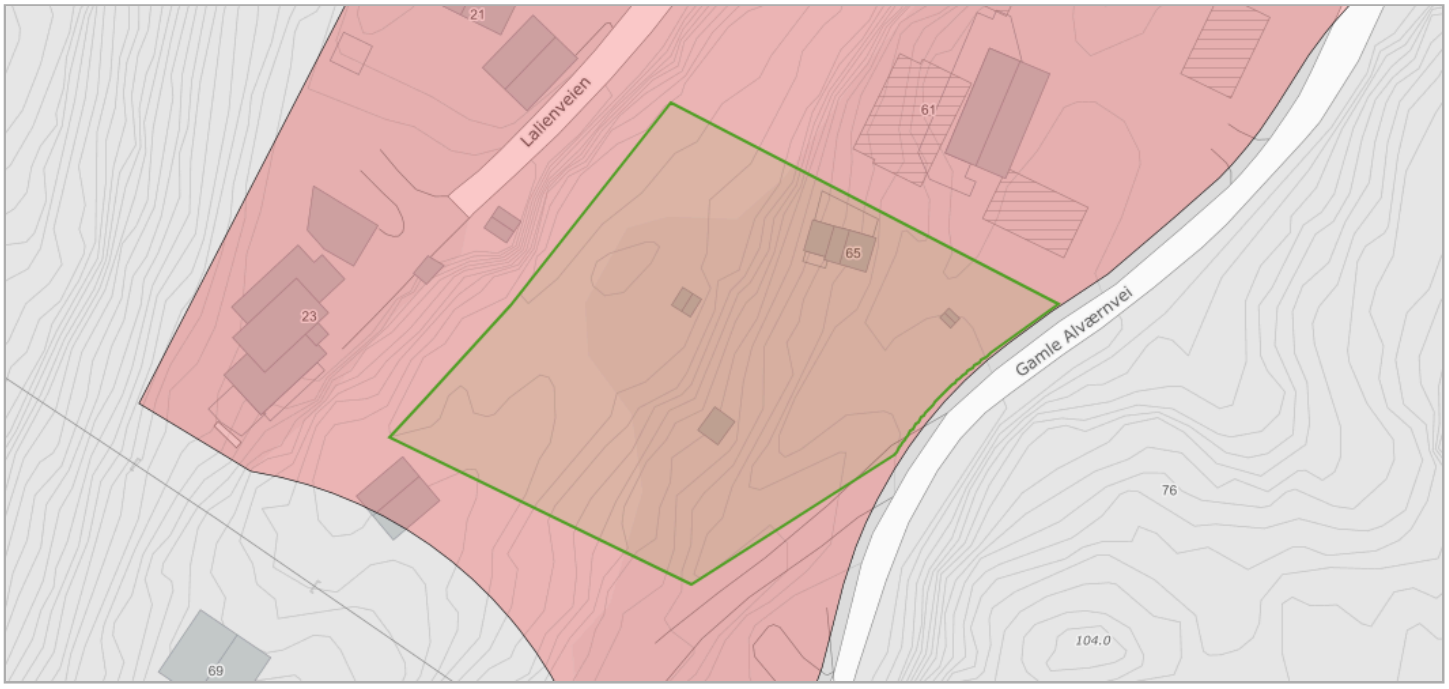

Om datasettet

Tettsteder er geografiske områder som har en dynamisk avgrensing, og antall tettsteder og deres yttergrenser vil endre seg over tid avhengig av byggeaktivitet og befolkningsutvikling.

Tegnforklaring

Tettsteder
Tettsteder

Et tettsted er en hussamling med minst 200 bosatte og der avstanden mellom husene normalt ikke skal overstige 50 meter. Les mer om tettsted og fullstendig definisjon her: http://www.ssb.no/beftett.

Objekter

Tettstednr	Navn	Innbyggere	Areal
0541	Nesoddtangen	13363	6.340160545748463